Reporte de Cambios 2022-09-02

Iconos en barra de navegación

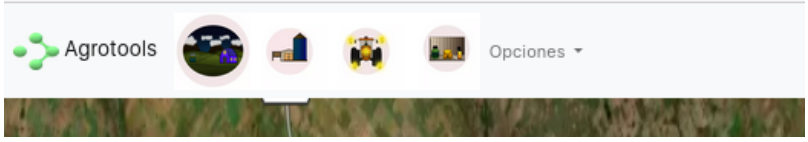

Iconos de actividades en el detalles de lotes

Los botones de "siembra", "aplicacion", etc. fueron reemplazados por los iconos provistos.

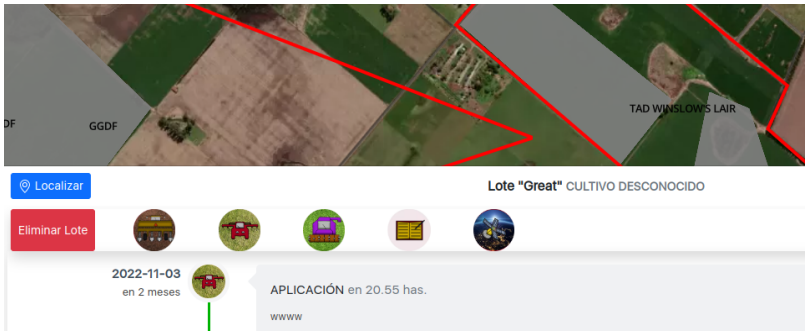

Nombres en polígono de campo

Ahora sobre el mapa aparece el nombre del campo.

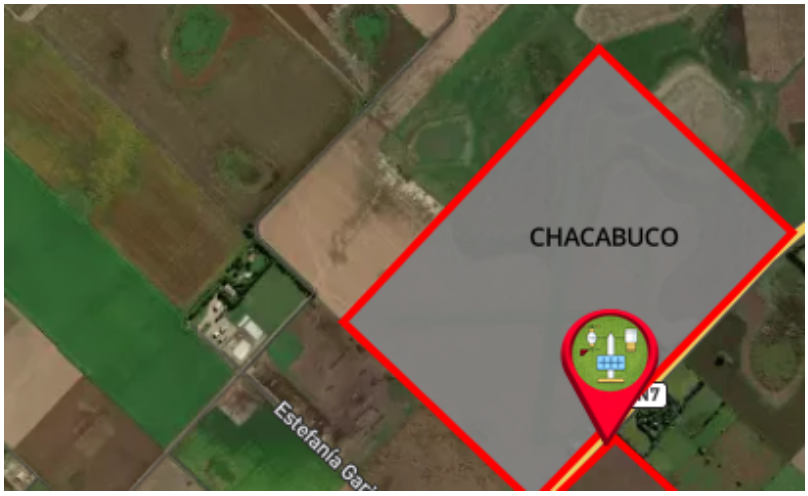

Panel de Sensores de humedad

Nuevo Panel con los graficos e imagen de fondo.

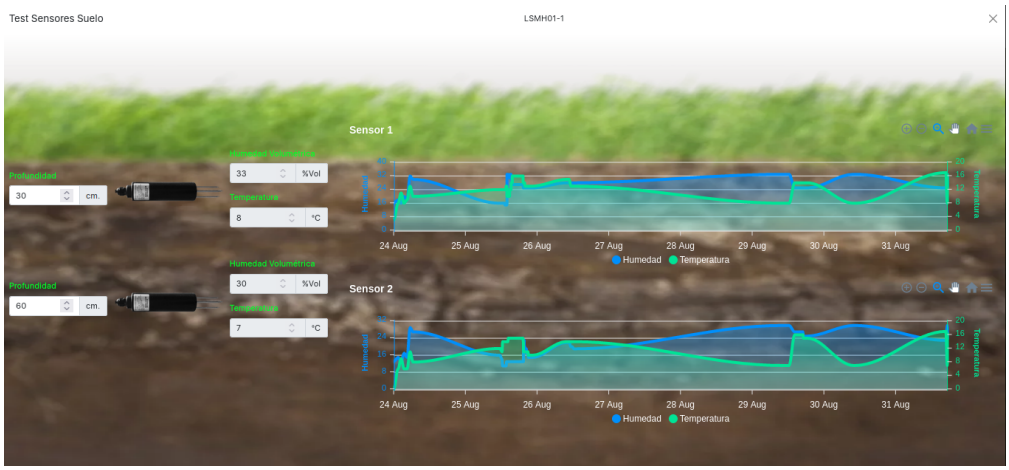

Datos Meteorológicos asociados a actividades

Cada actividad ahora tiene un botón donde se puede acceder a un listado de la centrales con los datos correspondientes a la fecha consignada en la actividad y la distancia desde el campo a la central en cuestión.

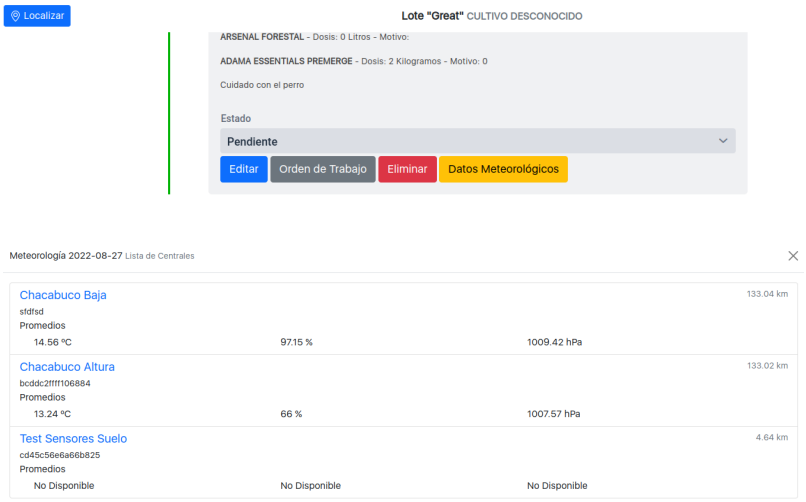

En caso de tratarse de una actividad planificada, aparece un mensaje acorde. (En el futuro se puede mostrar el pronostico)

Cambio en el panel de Centrales

Ahora los datos de las centrales usan iconos y muestra los gráficos con la imagen de fondo provista.

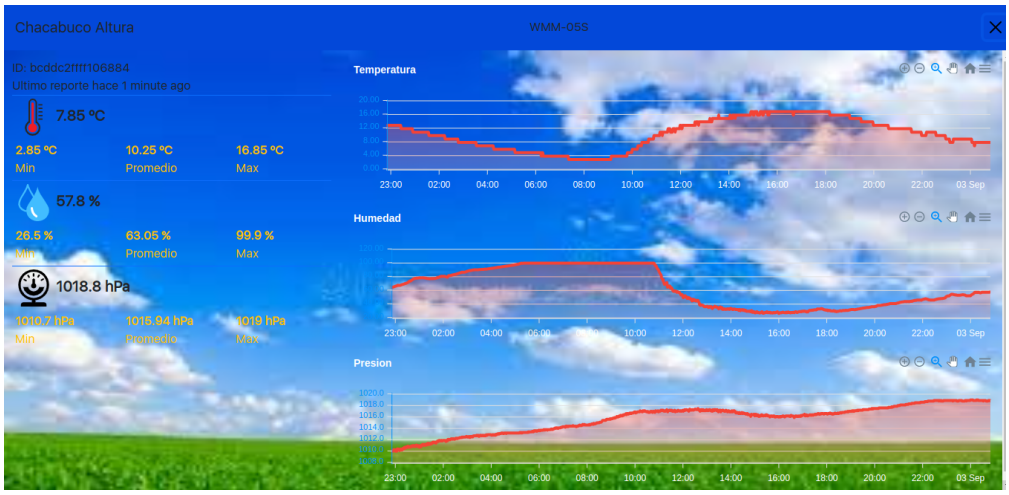
Chacabuco Altura
WMM-05S
ID: bcddc2fffr106884
Ultimo reporte hace 1 minute ago
7.85 ºC
2.85 ºC
Min
10.25 ºC
Promedio
16.85 ºC
Max
57.8 %
26.5 %
Min
63.05 %
Promedio
99.9 %
Max
1018.8 hPa
1010.7 hPa
Min
1015.94 hPa
Promedio
1019 hPa
Max
Temperatura
Humedad
Presion
23:00
02:00
04:00
06:00
08:00
10:00
12:00
14:00
16:00
18:00
20:00
22:00
03 Sep