Reporte de Cambios 2022-09-19

Exportación Gráficos -> Excel

Sobre cada gráfico, en el menu hay una opcion "Download XLS" que descarga la serie del gráfico correspondiente en formato "XLS".

Botón de descarga

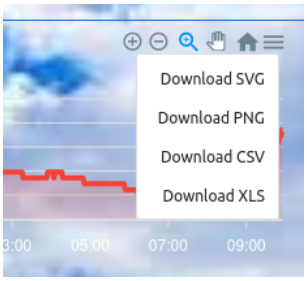

Archivo XLS

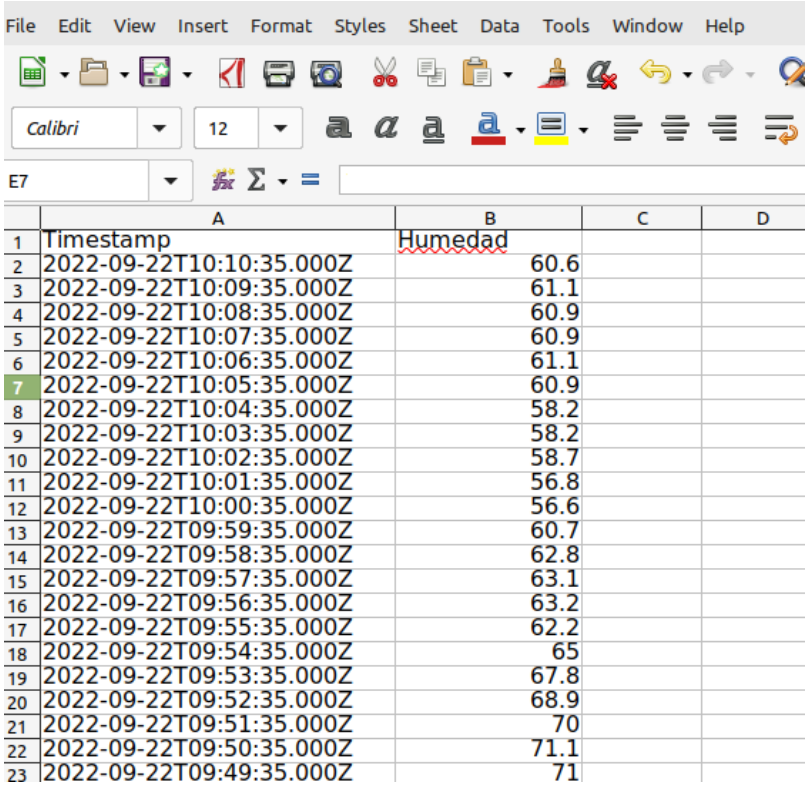

	A	B	C	D
1	Timestamp	Humedad		
2	2022-09-22T10:10:35.000Z	60.6		
3	2022-09-22T10:09:35.000Z	61.1		
4	2022-09-22T10:08:35.000Z	60.9		
5	2022-09-22T10:07:35.000Z	60.9		
6	2022-09-22T10:06:35.000Z	61.1		
7	2022-09-22T10:05:35.000Z	60.9		
8	2022-09-22T10:04:35.000Z	58.2		
9	2022-09-22T10:03:35.000Z	58.2		
10	2022-09-22T10:02:35.000Z	58.7		
11	2022-09-22T10:01:35.000Z	56.8		
12	2022-09-22T10:00:35.000Z	56.6		
13	2022-09-22T09:59:35.000Z	60.7		
14	2022-09-22T09:58:35.000Z	62.8		
15	2022-09-22T09:57:35.000Z	63.1		
16	2022-09-22T09:56:35.000Z	63.2		
17	2022-09-22T09:55:35.000Z	62.2		
18	2022-09-22T09:54:35.000Z	65		
19	2022-09-22T09:53:35.000Z	67.8		
20	2022-09-22T09:52:35.000Z	68.9		
21	2022-09-22T09:51:35.000Z	70		
22	2022-09-22T09:50:35.000Z	71.1		
23	2022-09-22T09:49:35.000Z	71		

NDVI - Cambio de formato y ubicación de la ventana.

La ventana de NDVI ahora aparece en la izquierda con un nuevo formato de las tarjetas de observaciones. Antes estaba en el sector inferior.

Vista general

Detalle de la observación seleccionada

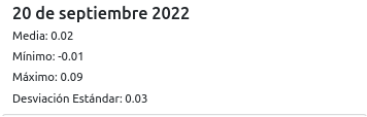

Tarjetas con indicación de nubosidad si correspondiere.

NDVI - Nueva escala con rango dinamico min-max.

Se puede elegir ver las imagenes en la escala tradicional que mapea ROJO-AMARILLO-VERDE -> -1..0..1 o en la escala dinámica que va desde AZUL-ROJO-VERDE -> mínimo valor de NDVI...máximo valor de NDVI (para esa observación).

Botones selectores de escala:

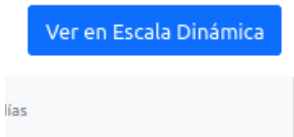

2

Ej: Escala Fija

Ej: Escala Dínamica

NDVI - Leyenda de Color.

Ahora existe una leyenda de color para cada escala.

Escala Fija



Escala Dinámica

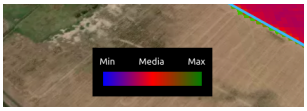

NDVI - Descarga de la imagen NDVI.

Se puede tambien descargar la imagen NDVI que se esta visualizando en formato PNG mediante el botón ubicado en el borde superior.

'I Descargar Img

e septiembre 2022